# R36
# МОКРІ АБО ВОЛОГІ МЕЗОТРОФНІ ТА ЕВТРОФНІ ПАСОВИЩА
# MOIST OR WET MESOTROPHIC TO EUTROPHIC PASTURE

Загальний вигляд біотопу, заплава р. Ікопоть, Хмельницька обл.

Вигляд біотопу із квадрокоптера, заплава р. Горинь, Рівненська обл.

## Опис біотопу

До цього типу належать пасовища або витоптувані луки, що формуються на мезотрофних або евтрофних, вологих або мокрих ділянках у помірній зоні Європи. Такі луки мають природне поширення у заплавах річок або по берегах рівнинних озер, на слабо дренованих місцях, що випасаються дикими тваринами або великою рогатою худобою. Вони можуть також формуватися в антропогенно змінених місцях, таких як береги меліоративних каналів, та на місцях постійного утримання худоби, які заливаються на тривалий час. Ґрунти можуть бути різними – глинистими, піщаними, торф'янистими, інколи солонуватими. Ділянки, зайняті цим біотопом, у зимовий період і навесні переважно затоплені, але висихають влітку. Найбільше поширення вони мають у заплавах річок і можуть займати досить значні площі, що зазнають природного заплавного режиму. Зарегулювання річкового стоку викликає скорочення площ, зайнятих цим типом. З іншого боку, інтенсивне випасання може впливати на видовий склад таких біотопів на понижених і особливо витоптуваних місцях. Для таких ділянок характерними є види, що витримують тривале затоплення (і витоптування), такі як *Argentina anserina, Trifolium fragiferum, T. repens, Plantago major, Agrostis stolonifera, Mentha pulegium*. Вони розвиваються і цвітуть впродовж сухого періоду. Деякі з них здатні швидко займати відкриті місця завдяки наявності столонів та кореневищ. Інші види цих угруповань особливо стійкі до випасу, оскільки вони неїстівні, такі як *Juncus effusus* або *Rumex crispus*. Більшість характерних видів цього біотопу є широко розповсюдженими, але деякі мають обмежене поширення. Серед них *Hydrocotyle vulgaris, Blysmus compressus, Carex secalina, Teucrium scordium.* Цей тип включає деякі види, які також характерні для піонерних угруповань берегів річок, з якими цей тип утворює мозаїку і перехідні стадії, але загалом угруповання цього типу є більш зімкнутими. На більш підвищених ділянках він може утворювати мозаїку з пасовищами союзу *Cynosurion cristati* (тип R21) або вологими чи мокрими сінокосами (тип R35). Деякі інші види, такі як *Mentha longifolia,* є спільними з високотравними угрупованнями вологих місцезростань (тип R55).

Цей тип біотопу є широко розповсюдженим у рівнинних регіонах помірної зони Європи. У більшій частині Середземноморського регіону він заміщується типом R32 (Середземноморські низькотравні вологі луки низовин). У континентальній частині Європи цей тип є рідкісним і обмежений ділянками з довготривалим високим рівнем води. Подібні угруповання поширені на солонуватих підвищених частинах Атлантичних та Прибалтійських солончаків, але у цьому випадку вони належать до приморської групи біотопів. Внутрішньоконтинентальні галофітні угруповання не належать до цього типу, оскільки вони розглядаються в межах галофітної групи.

Хоча цей тип досі має значне поширення у рівнинних регіонах помірної зони Європи, спостерігаються значні втрати його площ та зміни структури угруповань. Охорона або відновлення найкраще збережених ділянок вимагає підтримання належних гідрологічних умов та режимів випасу низької інтенсивності.

**Індикатори оптимального стану:**

- природний заплавний режим;
- тривалий період затоплення у зимовий період і навесні;
- підтримання пасовищного навантаження;
- відсутність чужорідних видів рослин.

**Характерні види**

**Рослини**

**Судинні рослини:** *Agrostis stolonifera, Argentina anserina, Carex hirta, Lolium perenne, Plantago major, Ranunculus repens, Schedonorus pratensis, Taraxacum* sect. *Taraxacum, Trifolium fragiferum, Deschampsia cespitosa*

**Мохоподібні:** *Calliergon cordifolium, Brachythecium mildeanum, Drepanocladus aduncus*

**Лишайники:** не характерні

**Рідкісні види:** *Angelica palustris*, Bupleurum tenuissimum*, Carex lsecalina*, Dactylorhiza incarnata*, Gladiolus tenuis*, Hydrocotyle vulgaris*, Leucojum vernum*, Salix myrtilloides**

**Чужорідні види рослин:** *Oxalis stricta, Galinsoga parviflora, Xanthium spinosum, Bidens frondosa, Juncus tenuis, Erigeron annuus, Trifolium hybridum*

**Тварини**

**Молюски:** *Zonitoides nitidus, Succinea putris, Fruticicola fruticum, Pseudotrichia rubiginosa, Carychium minimum*

**Комахи:** *Lycaena dispar**, Euthrix potatoria, Euclidia mi, Plusia festucae, Simyra albovenosa, Deltote uncula, Amphipoea fucosa, Lacanobia splendens, Mythimna impura*

**Земноводні:** *Bombina bombina**, Rana arvalis, Hyla orientalis*

**Плазуни:** *Natrix natrix, Zootoca vivipara, Lacerta agilis*

**Птахи:** *Circus pygargus***,* (*C. aeruginosus***), *C. cyaneus**** (Полісся, дуже рідкісний), *Acrocephalus paludicola***, A. schoenobaenus, Locustella naevia, L. fluviatilis, Anthus pratensis, Motacilla* (*citreola*) *werae, Tringa totanus,* (*Numenius arquata**), *Tringa stagnatilis*, Gallinago media***, G. gallinago, Crex crex**, Vanellus vanellus,* (*Motacilla flava, M. alba*), *Saxicola rubetra, S. rubicola, Sylvia communis*

**Ссавці:** *Neomys anomalus*, N. fodiens*

**Класифікації біотопів**
**UkrBiotop**
E:1.111 Щучникові луки, що формуються в умовах закислення ґрунту в негативних формах рельєфу
E:1.121 Вологі луки пасовищного використання
**Національний каталог біотопів України**
T3.2 Вологі луки пасовищного використання
**EUNIS (old)**
E3.44 Flood swards and related communities / Заливні луки і пов'язані з ними угруповання
**Резолюція 4 Бернської конвенції**
E3.4 Moist or wet eutrophic and mesotrophic grasslands / Мокрі або вологі евтрофні і мезотрофні луки
**Додаток I Оселищної Директиви —**

## Характерні види судинних рослин

Перстач гусячий
(*Argentina anserina*)

Жовтець повзучий
(*Ranunculus repens*)




Мітлиця повзуча
(*Agrostis stolonifera*)

Конюшина суницеподібна
(*Trifolium fragiferum*)




Подорожник великий
(*Plantago major*)

Осока шорстковолосиста
(*Carex hirta*)

Пажитниця багаторічна
(*Lolium perenne*)

Кульбаба лікарська
(*Taraxacum officinale*)

Щучник дернистий
(*Deschampsia cespitosa*)

Костриця лучна
(*Schedonorus pratensis*)

## Характерні види мохоподібних

Серпник гачкуватозігнутий
(*Drepanocladus aduncus*)

## Рідкісні види

Маточник болотний
(*Angelica palustris*)

Ласкавець найтонший
(*Bupleurum tenuissimum*)

Щитолисник звичайний
(*Hydrocotyle vulgaris*)

Осока житня
(*Carex secalina*)

Косарики тонкі
(*Gladiolus tenuis*)

Білоцвіт весняний
(*Leucojum vernum*)

## Чужорідні види рослин

Череда листяна
(*Bidens frondosa*)

Злинка однорічна
(*Erigeron annuus*)

Незбутниця дрібноцвіта
(*Galinsoga parviflora*)

Злинка канадська
(*Erigeron canadensis*)

Квасениця пряма
(*Oxalis stricta*)

Ситник тонкий
(*Juncus tenuis*)

Нетреба колюча
(*Xanthium spinosum*)

## Характерні види тварин

### Молюски

Бурштинка звичайна
(*Succinea putris*)

Равлик чагарниковий
(*Fruticicola fruticum*)

Кущанка волохата
(*Pseudotrichia rubiginosa*)

Мізунчик звичайний
(*Carychium minimum*)

### Комахи

Совка-листовійка бура
(*Deltote uncula*)

Евклідія конюшинова сіра
(*Euclidia mi*)

Кононопряд трав'яний
(*Euthrix potatoria*)

Совка рожево-бура
(*Lacanobia splendens*)

Дукачик непарний
(*Lycaena dispar*)

### Земноводні

Кумка червоночерева
(*Bombina bombina*)

Квакша східна
(*Hyla orientalis*)

### Плазуни

Ящірка живородна
(*Zootoca vivipara*)

Вуж звичайний
(*Natrix natrix*)

## Птахи

Деркач
(*Crex crex*)

Чайка чубата
(*Vanellus vanellus*)

Очеретянка лучна
(*Acrocephalus schoenobaenus*)

Плиска жовта
(*Motacilla flava*)

Коловодник ставковий
(*Tringa stagnatilis*)

Кобилочка річкова
(*Locustella fluviatilis*)

Лунь очеретяний
(*Circus aeruginosus*)

## Синтаксономія

***Molinio-Arrhenatheretea*** Tx. 1937
*Molinietalia caeruleae* Koch 1926
*Mentho longifoliae-Juncion inflexi* T. Müller et Görs ex de Foucault 2009
*Potentillo-Polygonetalia avicularis* Tx. 1947
*Potentillion anserinae* Tx. 1947

## Фітоіндикація (за шкалами Я.П. Дідуха)

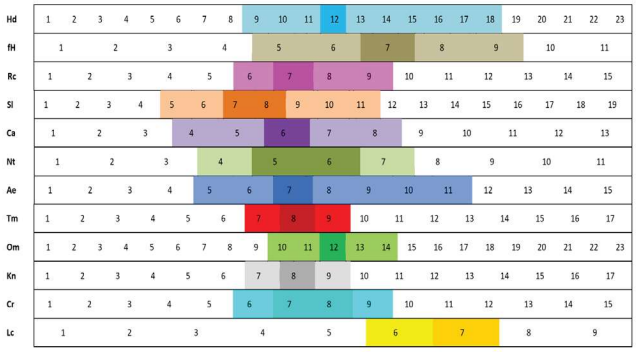


## Загрози

Основними загрозами є інтенсифікація сільського господарства (внесення добрив, осушення) і зміни гідрологічного режиму основних річкових систем Європи, наприклад, Дунаю, Рейну, Дніпра. Перевипас призводить до швидкої деградації біотопів унаслідок руйнування дернини. Інші основні втрати цього типу біотопу відбуваються через пряме руйнування біотопів (наприклад, внаслідок урбанізації).

## Охорона і менеджмент

Хоча такі пасовища все ще залишилися на досить значних площах, існують постійні ризики їх подальшої деградації. Для збереження досі існуючих біотопів цього типу необхідною умовою є збереження відповідних гідрологічних умов. Щоб відновити деградовані луки, тиск від сільськогосподарського використання (внесення добрив) повинен бути зменшений.

## Поширення в Україні

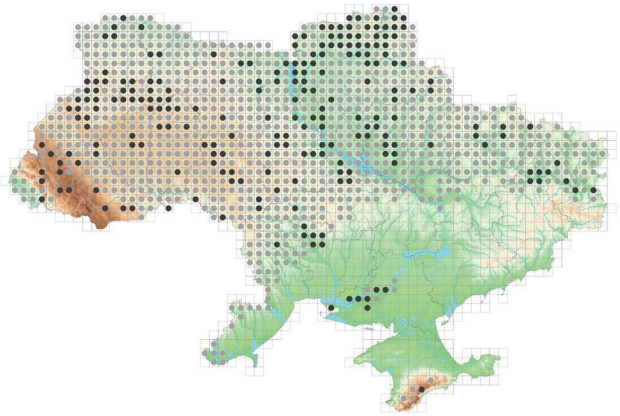

## Оцінка значимості та ризику втрат

| Категорії оцінки впливу загроз | | | | Сума балів оцінки загроз | Ступінь стійкості | Клас стійкості | Категорії созологічної значимості | | | | | | | | | | Сума балів созологічної цінності | Цінність біотопів, % | Клас цінності біотопів | Оцінка ризику втрат біотопів | Клас ризику втрат біотопів |
|---|---|---|---|---|---|---|---|---|---|---|---|---|---|---|---|---|---|---|---|---|---|
| a | b | c | d | | | | e | f | g | h | i | j | k | l | m | n | | | | | |
| 2 | 3 | 2 | 2 | 9 | 42 | III | 3 | 1 | 2 | 2 | 1 | 3 | 2 | 2 | 2 | 1 | 19 | 30 | IV | 51 | IV |

## Оцінка за критеріями МСОП:

| Інтегрована оцінка | Критерії Європейського червоного списку біотопів | | | | | | | | | | |
|---|---|---|---|---|---|---|---|---|---|---|---|
| | A1 | A2a | A2b | A3 | B1 | B2 | B3 | C/D1 | C/D2 | C/D3 | E |
| **EN** | VU | VU | VU | LC | LC | NT | LC | VU | EN | VU | LC |

Загальний вигляд біотопу, заплава р. Десна, Чернігівська обл.